Un modelo flexible para la simulación de distribución de ciudades

Pablo Ramírez, Paul Leger y Andrés Vallone
Escuela de Ciencias Empresariales
Universidad Católica del Norte
Coquimbo, Chile
Email: prl012@alumnos.ucn.cl, pleger@ucn.cl, avallone@ucn.cl

***Resumen*—El cumplimiento de la ley de *Zipf* es ampliamente reconocido en la literatura de economía urbana, al punto de utilizar su coeficiente, llamado Zipf, como medida de concentración espacial de la población. Mientras el exceso de concentración presenta problemas al bienestar social debido a la existencia de disparidades regionales y congestión de algunas ciudades, la dispersión no aprovecha, por ejemplo, los beneficios en la disminución de los costos de producción/transporte producidos por las economías de escalas.**

Diversos trabajos se han realizado a fin de dar una explicación al cumplimiento a la ley de Zipf, donde los modelos *top-down*, que fuerzan el cumplimiento de la ley de Zipf, dominan la literaria. Pocos trabajos han intentado explicar el cumplimiento de Zipf usando autómatas celulares. Estas propuestas, llamadas *bottom-up*, generan de manera emergente la distribución y los tamaños de las ciudades. Sin embargo, estos modelos son poco flexibles y no pueden ser adaptados a distintos sectores geográficos.

Este trabajo propone una implementación inicial de un modelo extensible basado en autómatas celulares, llamado CityCA, para intentar explicar el coeficiente de Zipf. Nosotros evaluamos y adaptamos CityCA a un escenario real, Chile. Con este modelo, los economistas urbanos no tienen que saber mucho de programación para usarlo, pues este modelo especializado ya contiene el conocimiento. Los resultados muestran la efectividad de las configuraciones hechas para el caso de estudio. Además, surgen nuevos requerimientos que se planean incorporar en un trabajo futuro de CityCA.

***Index Terms*—Ley de Zipf, Distribución de ciudades, Autómatas Celulares, City-CA.**

I. Introducción

La observación empírica muestra que las ciudades difieren en cuanto al tamaño y a las actividades que realizan. La distribución de las ciudades se forma con la aglomeración y desaglomeración de las personas, quienes eligen un lugar para establecerse según los beneficios que le otorga aquel lugar.

A medida que un país se desarrolla y disminuyen los costos de transporte, la población tiende a concentrarse espacialmente a fin de aprovechar los beneficios inherentes a la cercanía (*ej.* la mejora en los encadenamientos productivos y el incremento en los tamaño de los mercados). Sin embargo, la excesiva aglomeración genera efectos negativos (*ej.* congestión, contaminación). Por otro lado, la dispersión no permite obtener los beneficios de la concentración espacial.

Una de las medidas de concentración espacial de la actividad es el coeficiente del *Zipf*, el cual es derivado de la ley de *Zipf* [19] o regla rango-tamaño. La ley de Zipf se cumple si al ordenar todas las ciudades de mayor a menor según su tamaño, la ciudad de mayor tamaño tendrá aproximadamente el doble de población que la segunda, el triple que la tercera y así sucesivamente. Según esta regla, el coeficiente de Zipf será igual a uno si se cumple plenamente la ley, menor a uno si existe mayor dispersión y mayor a uno si hay más concentración en torno a la ciudad de mayor tamaño.

Al cumplirse la ley de Zipf, las ciudades se distribuyen de tal forma que se logra sacar provecho de los beneficios de la concentración espacial, si no se cumple, se pueden desaprovechar estos beneficios (dispersión) o generar problemas de exceso de concentración.

Actualmente no se dispone de una teoría que explique de manera concluyente la ley de Zipf. Las principales líneas de investigación tienden a explicar la ley con modelos matemáticos de tipo *Top-Down*, las cuales generalizan el comportamiento de distribución de los tamaños de las ciudades partiendo con el condicionante cumplimiento de la ley de Zipf. Es decir, estos modelos no explican como se genera la ley Zipf, sino que ellos asumen que Zipf se cumple y buscan qué comportamientos de la población satisfacen esta ley.

Algunos trabajos [13], [15] usan modelos *bottom-up* para tratar explicar la ley de Zipf a través de una conducta emergente y no impuesta. Estos modelos usan autómatas celulares (ACs) [14]. Los agentes de un AC representan empresas/personas que se relacionan entre ellas con el fin de reducir sus costos y maximizar sus beneficios. Sin embargo, la implementación de estos modelos es poco flexible y no permite adaptar el modelo a diferentes escenarios con el fin de capturar territorios geográficos reales.

Nosotros proponemos una implementación inicial en Python acerca de un modelo flexible (y abierto) que permite explicar el tamaño de las ciudades y su distribución espacial. En este modelo, basado en autómatas celulares, el coeficiente de Zipf resulta de una propiedad emergente y no de una propiedad impuesta (es decir, Top-down). La implementación de este modelo, llamada CityCA, *absorbe* los conceptos asociados a la área de la economías urbana y permite a los usuarios adaptar flexiblemente su implementación para ajustarla a diferentes escenarios, por lo que no necesitan saber mucho sobre programación.

Estructura del artículo. La sección II introduce brevemente

los problemas asociados a las tamaños de ciudades y cómo Zipf es usado para medir el nivel de concentración espacial de éstas en un país. La sección III explica los principales conceptos de los autómatas celulares. En la Sección IV, se presenta CityCA. La Sección V presenta el uso de CityCA para el caso de estudio de Chile. Por último la Sección VI concluye el trabajo.

II. Distribución de ciudades

La elección de localización de las personas se basa en que el lugar escogido le otorga más beneficios que cualquier otro lugar. Este proceso tiende a generar naturalmente concentraciones de población en lugares geográficos determinados. Al concentrarse la población se genera eficiencia productiva debido al surgimiento de economías de escala y también se incrementan los mercados, ya que al aumentar la población, habrán más empresas debido a una mayor demanda de productos.

La concentración espacial genera beneficios, sin embargo, un exceso de ésta provoca un conjunto de efectos negativos. Los excesos de concentración de la población pueden presentar problemas tanto a nivel de eficiencia en el crecimiento de las economías [3], [8], [9], [17] como problemas en el bienestar social debido a la existencia de disparidades regionales [1]. Una sobreconcentración de la población produce un aumento en el precio del suelo debido a la escasez de terrenos y lugares para vivir [7], además causa congestión que se traduce en una pérdida de bienestar. [2]

En este proceso de agrupación y dispersión se construye el sitema urbano de un territorio, y es aquí donde se puede observar una regularidad típica de distribución urbana que es la ley de *Zipf* [19]. Este hecho estilizado postula que la relación entre el ranking y el tamaño de las ciudades sigue una distribución de probabilidad de Pareto, y su versión linealizada puede representarse como:

$$\log y = \log A - \alpha \log x$$

donde x es el número de habitantes de una ciudad; y es el ranking de la ciudad según el número de habitantes ordenado de mayor a menor; A y α son constantes. El coeficiente α, conocido como el coeficiente de Zipf, mide el grado de concentración de la población. Un $\alpha > 1$ indica que hay una dispersión tal que no permite acceder a los beneficios de la aglomeración. En cambio, un $\alpha < 1$ indica una alta concentración de la población. Para visualizar la ley de Zipf, se puede tomar el caso de Chile y ordenar las ciudades por número de habitantes[1]. Al graficar los resultados, se identificará claramente una tendencia lineal como se muestra en la figura 1.

Al estimar la regresión se obtiene:

$$\log y = 5{,}167753 - 0{,}7969709 * \log x$$

donde el coeficiente $\alpha \cong 0{,}8$, mostrando una concentración de población excesiva. Sin embargo, Gabbaix e Ioanides en [6]

[1]Se consideraron ciudades mayores a 5000 habitantes según lo considerado por el INE como ciudad con los datos del Censo 2002.

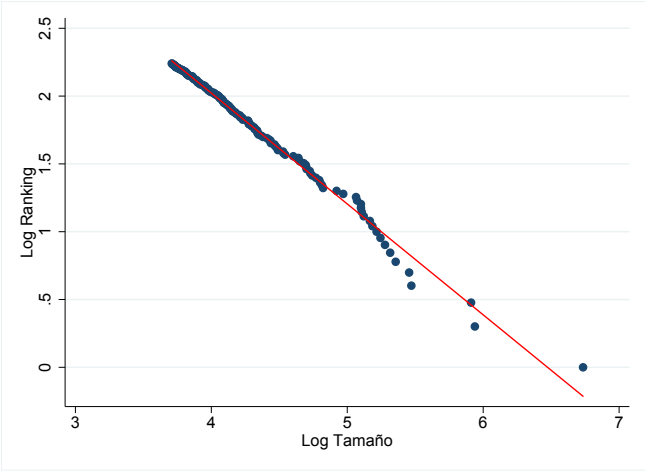

Figura 1. Gráfico del logaritmo del Ranking (por población) v/s el logaritmo del tamaño de la población. Chile, CENSO 2002.

sostiene que empíricamente se cumple la ley de Zipf para un coeficiente α entre $0{,}8$ y $1{,}2$, situando a Chile en el límite inferior del cumplimiento. La Ley de Zipf se ha transformado en un condicionante de los modelos de crecimiento urbano, puesto que en última instancia independientemente del factor asociado al crecimiento de la ciudades, la distribución final del tamaño de las ciudades debe seguir la ley de rango-tamaño [5]. En los modelos de crecimiento urbano que contemplan el surgimiento de la ley de Zipf, predominan aquellos basados en procesos estocásticos [18]. Sin embargo, en todos estos modelos el surgimiento de la ley es impuesto por construcción del modelo, desde una perspectiva *top-down*, es decir, van desde lo general a lo específico y ello requiere de una gran cantidad de parámetros para representar el comportamiento dinámico de los individuos. Con el tiempo estos modelos han intentando reflejar la realidad de manera más precisa y por lo tanto se han hecho más complejos aún.

Una forma alternativa de estimar un modelo tan complejo es simular el comportamiento individual de los actores participantes en él, es decir, desde una perspectiva *bottom-up*, donde se tiene más información del comportamiento individual que del general. Algunos trabajos [10], [14] usan instrucciones simples y cortas para cada individuo (o agente), en vez de tener que formular un modelo complejo desde el inicio. Por esto, un modelo basado en comportamiento individual se hace más conveniente al momento de simular comportamientos dinámicos complejos.

III. Autómatas Celulares

John Von Neumann en [14] propuso *Autómatas Celulares* (ACs) como un modelo matemático discreto con un poder de computabilidad equivalente a una máquina de Turing. Los ACs han sido usados en varios campos de las ciencias (*ej.* vida artificial[10], sistemas complejos [12], criptografía [16]). El *Juego de la Vida*[2] es un AC ampliamente conocido.

[2]http://es.wikipedia.org/wiki/Juego_de_la_vida

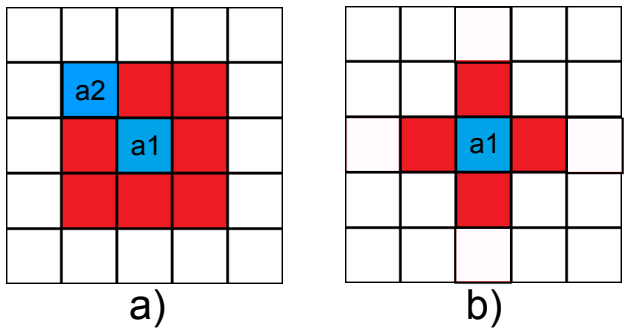

Figura 2. *a)* Dos agentes, usando la vecindad de Moore, en un AC. *b)* Un agente en un AC, el cual usa la vecindad de Neumann.

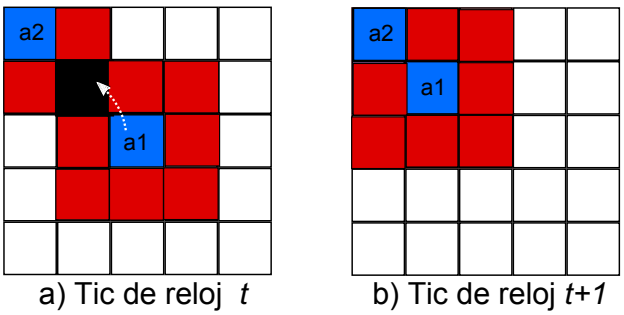

Figura 3. *a)* Un agente $a1$ en el tic de reloj t decide moverse cerca de $a2$. *b)* En el tic de reloj $t+1$, el agente $a1$ se encuentra más cerca del agente $a2$.

Tal como muestran las figuras 2a y 2b, un AC se compone de una grilla, la cual contiene un conjunto de agentes que interactúan con sus agentes vecinos con acciones simples. A continuación, describimos cada componente de un AC.

Grilla. Esta componente define el sector donde los agentes se albergan. Este sector está dividido en locaciones (*ej.* 25 locaciones en la figura 2a), las cuales contiene uno o más agentes. Una grilla puede ser uni-dimensional, bi-dimensional, incluso hasta tri-dimensional [10]. Además, una grilla puede tener características especiales, por ejemplo, puede ser finita, circular o infinita.

Agente. La figura 2a muestra dos agentes ($a1$ y $a2$) en una grilla, donde cada uno es un cuadrado azul. En ACs, un agente es una entidad que puede contener un estado y objetivo. El agente busca alcanzar su objetivo a través de las acciones que él puede tomar.

Vecindad. Cada agente tiene una vecindad. Esta vecindad determina cuáles son los elementos que afectan al estado y objetivo de un agente. Hay varios tipos de vecindades como *Moore* (figura 2a), la cual incluye las ocho locaciones más cercanas a un agente (locaciones rojas en la figura) más la locación del agente. Otro tipo de vecindad es la definida como *Neumman*, la cual involucra las cuatro celdas verticales y horizontales más cercanas además de la locación del agente (figura 2b). El número de locaciones que considera una vecindad depende de su *radio*. Por ejemplo, estas figuras muestran un radio de largo 1.

Acciones. En cada instante de tiempo discreto (conocido como "tic de reloj"), los agentes pueden ejecutar una acción dentro de un conjunto de potenciales acciones. La elección de una acción busca alcanzar su objetivo y obedecer las reglas del entorno. Por ejemplo, si el objetivo de un agente es estar cerca de otros agentes, un agente puede tomar la acción de moverse desde una locación x a una y si ésta última se encuentra más cerca de otros agentes. En ACs, se usa una función de *fitness* para determinar qué acción en un tic de reloj ayuda más a un agente a alcanzar su objetivo. Por ejemplo, la función de fitness que determina cuál locación ayuda más a un agente a a estar cerca de otros es:

$$nextLoc_a = \text{máx}_{[loc \ \in \ neighbors(radio_a)]} \, count(loc)$$

Donde se muestra que para cada locación de su vecindad, la función de fitness del agente a, cuenta el número de agentes cercanos. Luego, compara estos valores y selecciona la locación que contiene el mayor número de agentes cercanos.

La figura 3 ejemplifica el uso de la función de fitness presentada en la ecuación anterior. La figura 3a muestra que un agente $a1$ decide tomar la acción de moverse a la locación negra. La razón de esta decisión es debido a que su función de fitness entrega que la locación negra (dado su radio de locaciones disponibles) ayuda a alcanzar su objetivo en el tic de reloj t. En la figura 3b, se puede apreciar que el agente $a1$ se encuentra más cerca del agente $a2$ en el tic de reloj $t+1$.

IV. City-CA: Un AC flexible para determinar la distribución espacial de ciudades

Dentro de las aplicaciones que tiene un modelo de AC, se encuentra la simulación de interacciones dinámicas entre empresas (o personas). Con ACs, es posible estimar un punto de convergencia tras varias iteraciones, donde cada empresa se encontrará en un lugar del cual no quiera moverse. Así se puede determinar cuál será la distribución espacial y los tamaños de las ciudades de un sector geográfico en un país. Usando los tamaños de las ciudades, es posible calcular el coeficiente de Zipf (sección II).

CityCA es una implementación extensible de un modelo basado en ACs. CityCA es actualmente implementado en Python, un lenguaje *flexible*, orientado a objetos, dinámicamente tipeado y con soporte a funciones de primera clase y parámetros opcionales (como en Lisp). CityCA es usado para determinar el tamaño y distribución de las ciudades en un sector geográfico (generalmente, un país). Donde el tamaño es medido por el número de empresas en una misma ciudad. CityCA engloba los conceptos de economías urbanas en ciudades (*ej.* Zipf), dejando configurables (o abiertos al programador) los aspectos necesarios para adaptarse a características específicas de un sector geográfico. Usando la misma estructura de la sección anterior, nosotros explicamos cada componente de CityCA.

IV-A. Grilla

La idea de la grilla de este modelo es que se represente un sector geográfico real. Por tanto, cada casilla representa

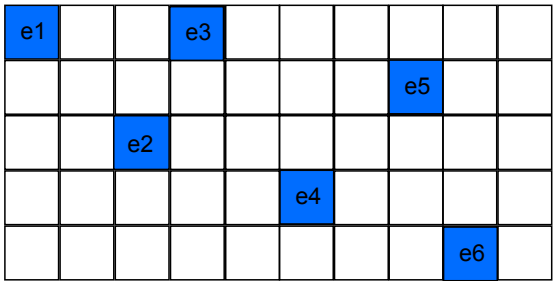

Figura 4. Una grilla de CityCA de cincuenta locaciones con seis empresas.

una cantidad específica de kilómetros cuadrados. La figura 4 muestra una grilla cuadrada de 50 locaciones. Por ejemplo, si cada locación representa un espacio de $0{,}1[km]$ de largo por $1[km]$ de alto, el sector geográfico total representado será de $5[km^2]$, ya que $(0{,}1[km] * 10) * (1[km] * 5) = 5[km^2]$. Es importante mencionar que el tamaño de una locación no es un elemento a considerar mientras no se analicen los procesos de formación de las ciudades. Solo ha de considerarse que el tamaño de una locación en relación al tamaño total de la grilla no sea excesivo al punto de perder representatividad del espacio geográfico a estudiar.

La grilla de CityCA es bi-dimensional y su tamaño puede ser configurado al momento de crearse un objeto del tipo CityCA. El tamaño de una grilla se configura indicando la cantidad de filas y de columnas. Por ejemplo, si se quiere una grilla de 30 filas por 25 columnas, se define:

```
chile = CityCA(30,25)
```

Aunque CityCA está orientado a simular sectores geográficos reales, estamos conscientes que ciertos experimentos buscan explorar comportamientos de formación de ciudades en escenarios imaginarios [13]. Por esta razón, la configuración de una grilla por omisión (finita y no circular) puede ser modificada:

```
chile = CityCA(30,25,CityCA.CIRCULAR_GRID)
```

CityCA ofrece un conjunto de estrategias para manejar una grilla (*ej.* circular, infinita).

IV-B. Agentes

Dentro de la economía urbana y en este artículo se plantea como supuesto que la relación empresa-persona es 1:1, es decir, una empresa equivale a una persona para generar modelos consistentes de la distribución de ciudades [11], [4].

En este modelo cada agente representa una empresa. Siguiendo con un sector geográfico real, una o más empresas pueden estar en la misma locación, donde la concentración de una locación es medida por el número de empresas que contiene. En CityCA, las empresas no contienen estados (por ahora), pero si tienen objetivos. El objetivo de cada empresa es disminuir sus costos y mejorar sus ingresos. Por ejemplo, el siguiente código crea e inserta 15000 empresas en un objeto CityCA.

```
chile.createCompanies(15000)
```

Algunas características de las empresas (*ej.* función de ajuste) pueden ser personalizadas al momento de crearlas. Estas características las explicamos en las próximas dos secciones.

IV-C. Vecindad

En la práctica, una empresa decide moverse con el objetivo de mejorar sus utilidades. En general, las mayoría de las empresas no pueden moverse rápidamente en una gran distancia por razones de infraestructura. Este límite de movimiento es el $radio$ de la empresa, el cual indica donde se puede mover en la siguiente iteración. El radio mínimo es 0, ya que se considera que una empresa podría no moverse debido a los costos implicados. El radio máximo posible es equivalente a la longitud máxima de la grilla[3]. En CityCA, cada empresa puede tener un radio distinto. Los radios pueden ser distribuidos en forma aleatoria entre un radio mínimo y un radio máximo. Por ejemplo, el siguiente código crea 15000 agentes con un radio al azar de distribución uniforme entre 1 y 15:

```
uniformDistribution = CityCA.Radium.uniform(1,15)
cityCA.createCompanies(15000,uniformDistribution)

"""Donde uniform de 'CityCA.Radium' es"""
def uniform(rmin,rmax):
  def radium():
    return random.uniform(rmin,rmax)
  return radium
```

La variable `uniformDistribution` es una función que retorna un valor entero al azar entre 1 y 15 cada vez que es evaluada[4]. Cuando las empresas son creadas cada una tiene asociada esta función de radio. Notar que `create` es la misma función del código mostrado en la sección IV-B, pero ahora con un argumento adicional, el cual es opcional (una cualidad de Python). Por omisión, todas las empresas se pueden mover a cualquier locación (es decir, tienen un radio del máximo de la grilla).

Para los programadores, una serie de funciones de librería para establecer radios están disponibles (*ej.* `normal`, la cual asigna radios usando la distribución normal). Adicionalmente, un programador puede definir su propia función para asignar radios. Por ejemplo, el siguiente código crea 15000 agentes con un radio fijo de 15:

```
def createFixedRadium(radio):
  def radium():
    return radio
  return radium

fixedRadium = createFixedRadium(15)
chile.createCompanies(15000,fixedRadium)
```

IV-D. Acciones

Las empresas deben tomar acciones que mejoren sus utilidades. En CityCA, las empresas usan la función de fitness para decidir que acción tomar, la cual básicamente es moverse a un lugar. Un programador de CityCA puede personalizar

[3]En el caso de que sea una grilla circular, el radio máximo sería: $r_{max} = Z/2$, donde Z equivale a la longitud máxima de la grilla

[4]Notar que la evaluación de `uniform` retorna otra función (*funciones de primera clase en Python*), la cual es la pasada por parámetro a `createCompanies`.

las funciones de ajustes de acuerdo a los requerimientos su experimento. Esta función es personalizada al momento de crear las empresas:

```
chile.createCompanies(15000,
      fitness=CityCA.fitness.betterToBeTogether)

"""Donde 'betterToBeTogether' es:"""
def betterToBeTogether(self,location):
  return location.countCompanies()
```

CityCA también ofrece a los programadores una librería de funciones de ajuste. Por ejemplo, en el código de arriba podemos ver que al momento de crear las compañias, la función `betterToBeTogether` es asignada como función de ajuste[5]. Con esta función, las empresas buscarán estar en locaciones con más empresas. La función `betterToBeTogether` sigue el principio que cuando hay más empresas juntas, los costos de transportes/producción disminuyen.

Como en las mayoría de las opciones de CityCA, los programadores pueden definir sus propias funciones de ajuste para las empresas. Por ejemplo, si deseamos que las empresas consideren los costos asociados a la concentración y congestión de empresas de una ciudad, un programador puede definir la siguiente función:

```
def itIsNotSoGoodToBeTogether(self,location):
  companiesNumber = location.countCompanies()
  factor = 0.25
  deglomeration = (factor*companiesNumber)**2
  return companiesNumber - deglomeration

"""Usando una funcion personalizada de fitness"""
chile.createCompanies(15000,
      fitness=itIsNotSoGoodToBeTogether)
```

La variable `deglomeration` representa el costo asociado a la concentración de empresas, y su `factor` o peso $(0,25)$, ha sido usado en otros trabajos (*ej.* [13]) para indicar como afecta la economía de desaglomeración.

IV-E. Ejecutando una Simulación en CityCA

Luego que se tiene una grilla con un conjunto de empresas distribuidas, donde cada una posee un determinado radio y una función de ajuste, CityCA permite a los programadores ejecutar una simulación. En esta simulación, las empresas comienzan a interactuar en cada iteración moviéndose al lugar que mejor evalúe según su función de ajuste.

Siguiendo los principios de un CA, las empresas se pueden mover una vez por cada tic de reloj. Para definir el número de iteraciones en CityCA, basta con especificar la cantidad deseada en el método `run` de un objeto CityCA. Por ejemplo, si se requiere de 20 iteraciones:

```
chile.run(20)
```

Usando la característica de *dynamic typing* de Python, un programador puede pasar una función (en vez de un número entero) que señale cuando se debe detener la simulación. Por ejemplo, si deseamos detener la simulación solamente cuando ninguna empresa se mueve en un tic de reloj:

[5]En Python, es posible mencionar qué argumento opcional se desea pasar como parámetro a una función.

```
def anyAgentMoved(previousCompanies,currentCompanies):
  boolean moved = False
  for pAgent in previousCompanies:
    for cAgent in currentCompanies:
      if  pAgent == cAgent:    """same companies?"""
        if not sameLocation(pAgent,cAgent):
          moved = True
  return moved

"""Simulando hasta que una condicion se cumpla"""
chile.run(anyAgentMoved)
```

La función `anyAgentMoved` recibe la lista de las empresas del tic de reloj $t-1$ y la lista de las empresas del tic de reloj t. Luego, empresa por empresa, se verifica si alguna ha cambiado de locación. Si ninguna ha cambiado de locación, la simulación se detiene, entregando un reporte gráfico acerca de las distribuciones de las ciudades y el coeficiente de Zipf asociado.

V. Chile: Caso de estudio de CityCA

En este caso de estudio se valida la flexibilidad de CityCA para adaptarse al territorio chileno y a la configuraciones que determinan las normas de comportamiento de los agentes. Estas configuraciones determinan el tamaño y la distribución de las ciudades a la que converge luego de n iteraciones.

Usando los conceptos de la sección anterior, nosotros mostramos el código necesario para llevar a cabo la simulación realizada en el caso de estudio.

```
1 uniformDistribution = CityCA.Radium.uniform(0,537)
2 fitness  = CityCA.fitness.betterToBeTogether
3 chile = CityCA(22,537)
4 chile.createCompanies(20000,uniformDistribution,fitness)
5 chile.run(anyAgentMoved);
```

A continuación, se explica la configuración de CityCA para el territorio chileno usando el código de arriba:

Vecindad. La distribución del radio se define en la línea de código número 1. El radio se fija con un mínimo de 0 y un máximo equivalente a la longitud máxima (537), puesto que es una malla finita, mientras que su distribución es aleatoria y uniforme.

Acciones. La función de ajuste se define en la línea de código número 2. La función asignada es `betterToBeTogether`, con la cual las empresas buscarán estar en locaciones que tengan la mayor cantidad de empresas.

Grilla. El tamaño de la grilla se define en la línea de código número 3. Para que los parámetros dimensionales se ajusten a la realidad geográfica de un país, es necesario saber el área de su superficie y la distribución del largo y ancho de ésta. En este caso, Chile cuenta con $756102{,}4[km^2]$ de superficie, mide entre $4270[km]$ y $4329[km]$ de largo y tiene un ancho promedio de $177[km]$ distribuidos entre $90[km]$ y $435[km]$[6]. Según estos datos, la configuración que difiere menos de la superficie real es una malla de $22*537$ locaciones de $8[km^2]$ cada una, lo que da un total de $756096[km^2]$, que representa un $99{,}9992\,\%$ del tamaño total real.

[6]https://es.wikipedia.org/wiki/Chile

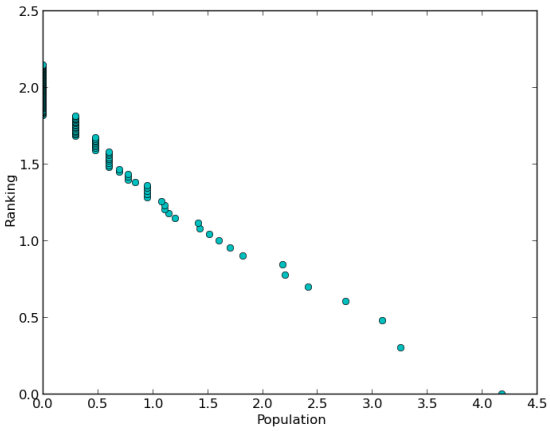

Figura 5. Resultado de la simulación.

El número de locaciones en una grilla solo influirá en el grado de especificación de los resultados, ya que mientras más subdividida sea la grilla, la información resultante será a un nivel más local. Sin embargo, éste número se vuelve irrelevante ya que no se puede considerar una locación como un espacio geográfico equivalente a una ciudad puesto que esta última puede ocupar varias casillas a la vez. Por último los límites de la grilla se consideran finitos para que corresponda a un límite fronterizo real.

Agentes. El número de empresas se define en la línea de código número 4, donde además se especifica la distribución y función de ajuste definida en las líneas anteriores. El número de agentes corresponde al número de empresas que tiene el país. En Chile existen aproximadamente 800.000 empresas: 8.000 grandes, 12.000 medianas, 120.000 pequeñas y 660.000 microempresas. Se considera la suma de las grandes y medianas empresas (20.000) que son las que poseen una mayor cuota de mercado en la economía y que atraen más personas.

Iteraciones. Por último, en la línea de código número 5, se define cuándo se detiene la simulación, la cual puede ser un número o una función. En este escenario, se usó 50 como máximo número de iteraciones.

Con solo estas 5 líneas de código es posible configurar el modelo para obtener los resultados de una simulación de las distribuciones de ciudades adaptadas a un territorio geográfico real como Chile. Para cualquier adaptación, solo se necesita cambiar algunas de estas lineas. Por ejemplo, si deseamos cambiar la función de fitness a `itIsNotSoGoodToBeTogether`, solamente debemos modificar la linea 2 a:

```
2 fitness = itIsNotSoGoodToBeTogether
```

V-A. *Resultados*

Los resultados de la simulación se muestran en la figura 5. La estimación de la regresión resultó:

$$\log y = 1{,}957183 - 0{,}5504229 * \log x$$

Las diferencias de intercepto son irrelevantes en términos de distribución espacial, ya que solo pueden indicar el tamaño de la población más grande estimada. El coeficiente de Zipf es $\alpha \cong 0{,}55$ e indica concentración espacial. Al comparar esta interpretación con la de la sección II, observamos que a pesar de que en ambos casos existe sobre concentración, el coeficiente calculado anteriormente es mayor ($\alpha \cong 0{,}8$). La diferencia en la estimación se debe a los parámetros escogidos para la simulación. La función de ajuste utilizada es `betterToBeTogether`, la cual permite a las empresas concentrarse en las locaciones con más empresas sin que exista un costo asociado a esta congestión. Naturalmente, esta configuración genera la sobre concentración y explica el valor del coeficiente de Zipf.

VI. Conclusiones & Trabajo Futuro

La distribución de los tamaños de las ciudades en un país es fundamental para evitar problemas de concentración y dispersión. Comprender las razones asociadas a esta distribución es todavía un problema no completamente resuelto [5]. En este trabajo, hemos propuesto CityCa, un modelo flexible y abierto basado en autómatas celulares para intentar explicar esta distribución. A diferencia de la mayorías de los modelos propuestos [5], [13], la distribución de los tamaños de las ciudades en CityCA es una propiedad emergente y no impuesta. Además, CityCA puede ser fácilmente personalizado para adaptarse a nuevos espacios geográficos (por ejemplo, países). Además se utilizó CityCA para determinar la distribución de los tamaños y espacial de las ciudades de Chile.

Este trabajo presenta una implementación inicial de CityCA, la cual puede dejar fuera requerimientos asociados a una mayor complejidad de estudios en base a territorios. Por ejemplo, los escenarios de CityCA no consideran la existencia de recursos naturales existentes en cada locación (*ej.* cobre en Chile), que afectan fuertemente las decisiones de localización de las empresas. Además, CityCA aún no considera el estado interno de cada empresa (*ej.* estabilidad), lo cual también podría afectar la decisión de acción de una empresa. Otra cualidad que no se incorporó en la versión actual de CityCA, es la explicación del proceso evolutivo de la generación de ciudades, ya que hasta ahora solo se considera la distribución final. En un futuro trabajo, planeamos incorporar en CityCA estas opciones de manera de ser configurables por el investigador.

Disponibilidad. Esta versión inicial de CityCA está disponible para su descarga en https://github.com/pleger/CityCA, un repositorio *Git* público para control de versiones de documentos/código fuentes.

Referencias

[1] Harvey Amstrong and Jim Taylor. *Regional Economics and Policy*. Wiley-Blackwell, 3 edition, August 2000.

[2] Jan K. Brueckner. Urban sprawl: Diagnosis and remedies. *International Regional Science Review*, 23(2):160–171, 2000.

[3] Marius Brülhart and Federica Sbergami. Agglomeration and growth: Cross-country evidence. *Journal of Urban Economics*, 65(1):48–63, January 2009.

[4] Masahisa Fujita, Paul Krugman, and Anthony J. Venables. *The Spatial Economy: Cities, Regions, and International Trade*, volume 1 of *MIT Press Books*. The MIT Press, June 2001.

[5] Xavier Gabaix. Zipf's law for cities: An explanation. *The Quarterly Journal of Economics*, 114(3):739–767, August 1999.

[6] Xavier Gabaix and Yannis M. Ioannides. The evolution of city size distributions. In J. V. Henderson and J. F. Thisse, editors, *Handbook of Regional and Urban Economics*, volume 4 of *Handbook of Regional and Urban Economics*, chapter 53, pages 2341–2378. Elsevier, April 2004.

[7] E. Helpman. The size of regions. Papers 14-95, Tel Aviv, 1995.

[8] J. Vernon Henderson. The effects of urban concentration on economic growth. NBER Working Papers 7503, National Bureau of Economic Research, Inc, January 2000.

[9] Vernon Henderson. How urban concentration affects economic growth. Policy Research Working Paper Series 2326, The World Bank, April 2000.

[10] Jarkko Kari. Theory of cellular automata: a survey. *Theoretical Computer Science*, 334(1-3):3–33, April 2005.

[11] Paul Krugman. Increasing returns and economic geography. *Journal of Political Economy*, 99(3):483–99, June 1991.

[12] Christopher G Langton. Studying artificial life with cellular automata. *Physica D: Nonlinear Phenomena*, 22(1–3):120 – 149, 1986. ¡ce:title¿Proceedings of the Fifth Annual International Conference ¡/ce:title¿.

[13] Yuri Mansury and Laszlo Gulyas. The emergence of Zipf's Law in a system of cities: An agent-based simulation approach. *Journal of Economic Dynamics and Control*, 31(7):2438–2460, 2007.

[14] John Von Neumann. *Theory of Self-Reproducing Automata*. University of Illinois Press, Champaign, IL, USA, 1966.

[15] Kwok Tong Soo. Zipf's law and urban growth in malaysia. *Urban Studies*, 44(1):1–14, 2007.

[16] Marco Tomassini and Mathieu Perrenoud. Cryptography with cellular automata. *Applied Soft Computing*, 1(2):151 – 160, 2001.

[17] Jeffrey G. Williamson. Regional inequality and the process of national development: A description of the patterns. *Economic Development and Cultural Change*, 13(4):1–84, July 1965.

[18] Zengwang Xu and Robert Harriss. A Spatial and Temporal Autocorrelated Growth Model for City Rank?Size Distribution. *Urban Studies*, 47(2):321–335, 2010.

[19] George Kingsley Zipf. *Human behavior and the principle of least effort*. Oxford, England: Addison-Wesley Press, 1949.